RADAPT

Guida all'uso della piattaforma

Adattamento climatico locale — Barigadu Guilcer

A cura di Rete Gaia Srl

Luglio 2026

Introduzione

Questa guida è rivolta ai referenti designati dai comuni e dagli enti del Barigadu Guilcer per la compilazione delle catene di impatto climatico e la pesatura degli indicatori, e ai coordinatori che gestiscono il lavoro del territorio. Descrive in dettaglio, passo per passo, ogni schermata della piattaforma RADAPT così come si presenta oggi.

La guida è divisa in due parti. La Parte 1 spiega come funziona la piattaforma in modo permanente: resta valida indipendentemente da quanto lavoro è già stato svolto. La Parte 2 fotografa lo stato di avanzamento del progetto al momento della stesura di questo documento, ed è quindi la parte destinata a cambiare più spesso.

Parte 1 — Come funziona la piattaforma

1. Accesso

L'accesso non richiede una password da ricordare: si effettua tramite un link personale ("magic link") inviato via email. Al primo utilizzo il link arriva dal coordinatore del territorio, che ha creato l'utenza; le volte successive è sufficiente richiedere un nuovo link dalla pagina di accesso con la stessa email.

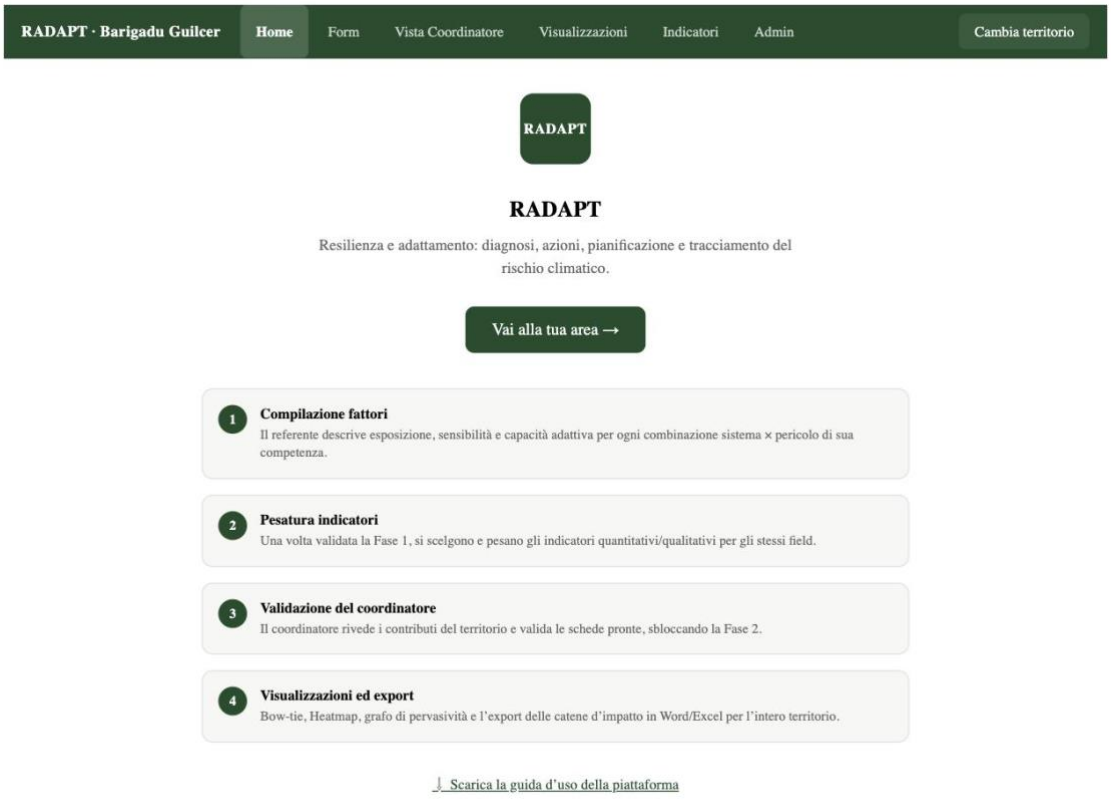

Home della piattaforma per il territorio Barigadu Guilcer.

Se si dispone dell'accesso a più di un territorio (per esempio Barigadu Guilcer e, in futuro, Comune di Sinnai), all'inizio di ogni sessione viene chiesto su quale territorio operare:

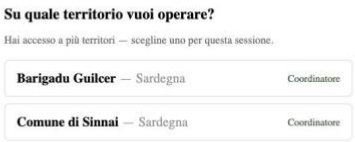

Selezione del territorio all'avvio della sessione.

È possibile cambiare territorio in qualsiasi momento dal link "Cambia territorio" in alto a destra nella barra di navigazione.

2. Ruoli

- Coordinatore — gestisce il territorio: assegna ai referenti le combinazioni sistema × pericolo × field di loro competenza, decide quali combinazioni della libreria sono attive per il territorio, valida i contributi inviati dai referenti e sblocca così la Fase 2, gestisce gli utenti.
- Referente — compila le catene di impatto (Fase 1) per le combinazioni assegnate e, una volta validate, pesa i relativi indicatori (Fase 2).
- Osservatore — accesso in sola lettura: può consultare visualizzazioni ed esportazioni ma non può compilare né modificare dati.

Un referente vede solo le combinazioni sistema × pericolo × field che il coordinatore ha attivato per il territorio e gli ha assegnato personalmente — non l'intera libreria dei fattori. L'assegnazione si fa dal pannello Admin, con selezione multipla: il coordinatore può scegliere più field in un solo passaggio invece di assegnarli uno alla volta.

3. Compilare una catena di impatto (Fase 1)

La compilazione segue quattro passaggi, sempre visibili in alto come indicatore di avanzamento: Selezione → Fattori → Pesatura → Note.

Passaggio 1 — Selezione

Si sceglie la combinazione da compilare tra sistema impattato, pericolo climatico e impact field, limitatamente a quelle assegnate. Quando alcuni field sono già stati validati dal coordinatore, in questa schermata compare anche un avviso che permette di passare direttamente alla pesatura degli indicatori.

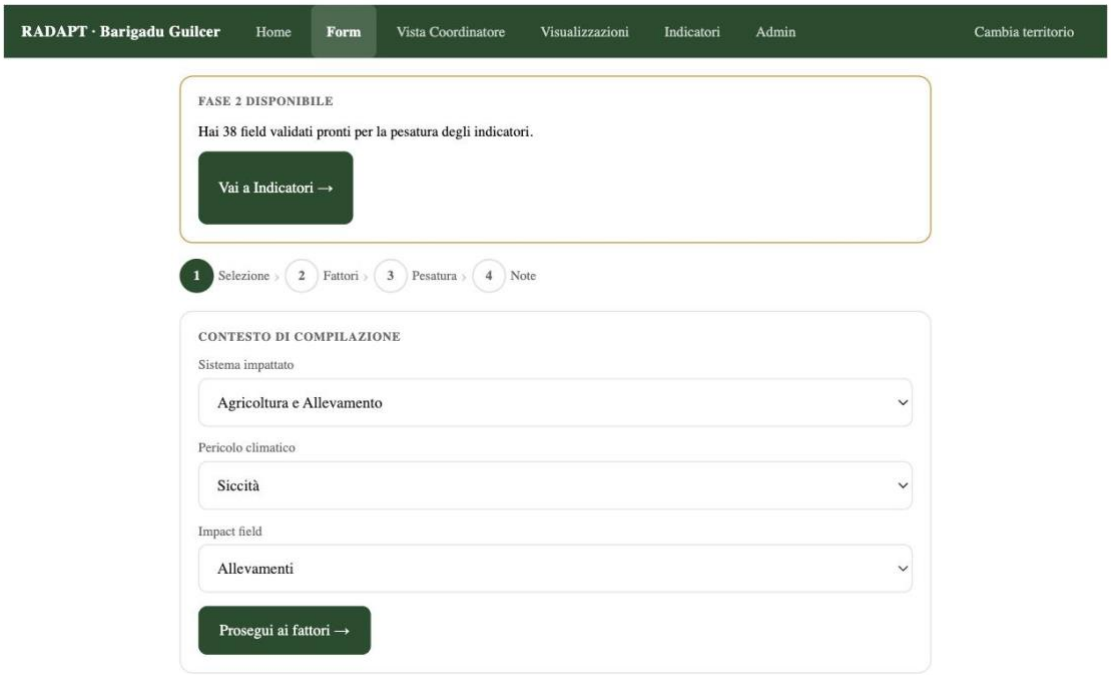

Passaggio 1 — Selezione della combinazione sistema × pericolo × field.

Passaggio 2 — Fattori

Per la combinazione scelta si selezionano i fattori pertinenti dalla libreria, raggruppati in tre categorie sempre nello stesso ordine: Esposizione, Sensibilità, Capacità adattiva (riconoscibili anche dal colore del riquadro — rispettivamente blu, rosso e verde). Se un fattore rilevante per il territorio non è presente in libreria, si può aggiungere liberamente con il campo "Aggiungi fattore specifico del territorio".

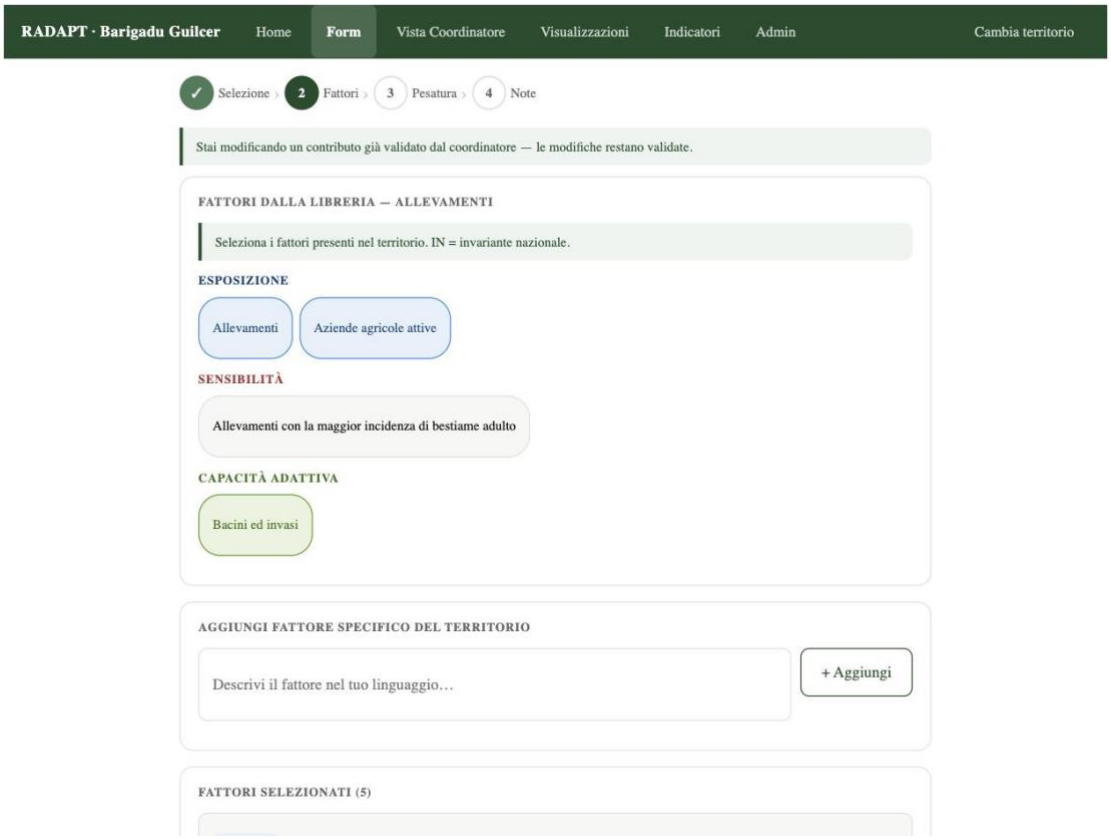

Passaggio 2 — Selezione dei fattori per categoria (Esposizione, Sensibilità, Capacità adattiva).

Ogni fattore selezionato — anche quelli aggiunti da altri referenti sulla stessa combinazione — ha uno spazio commenti dedicato, utile per porre una domanda al coordinatore o segnalare un dubbio senza bloccare la compilazione:

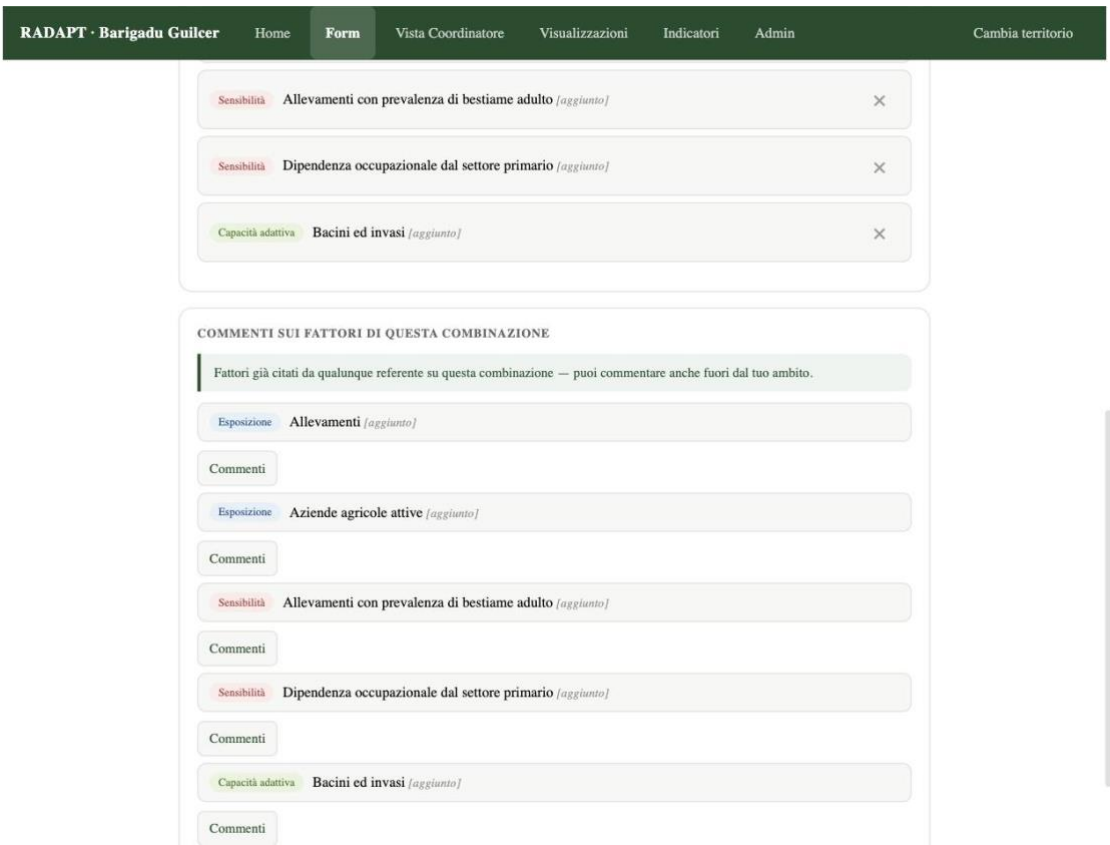

Commenti sui fattori di una combinazione, visibili a chiunque lavori su di essa.

Passaggio 3 — Pesatura

Solo i fattori di Sensibilità e Capacità adattiva vengono pesati, su una scala a tre livelli: Determinante (3), Rilevante (2), Marginale (1). L'Esposizione, essendo una descrizione fattuale del pericolo, non viene pesata.

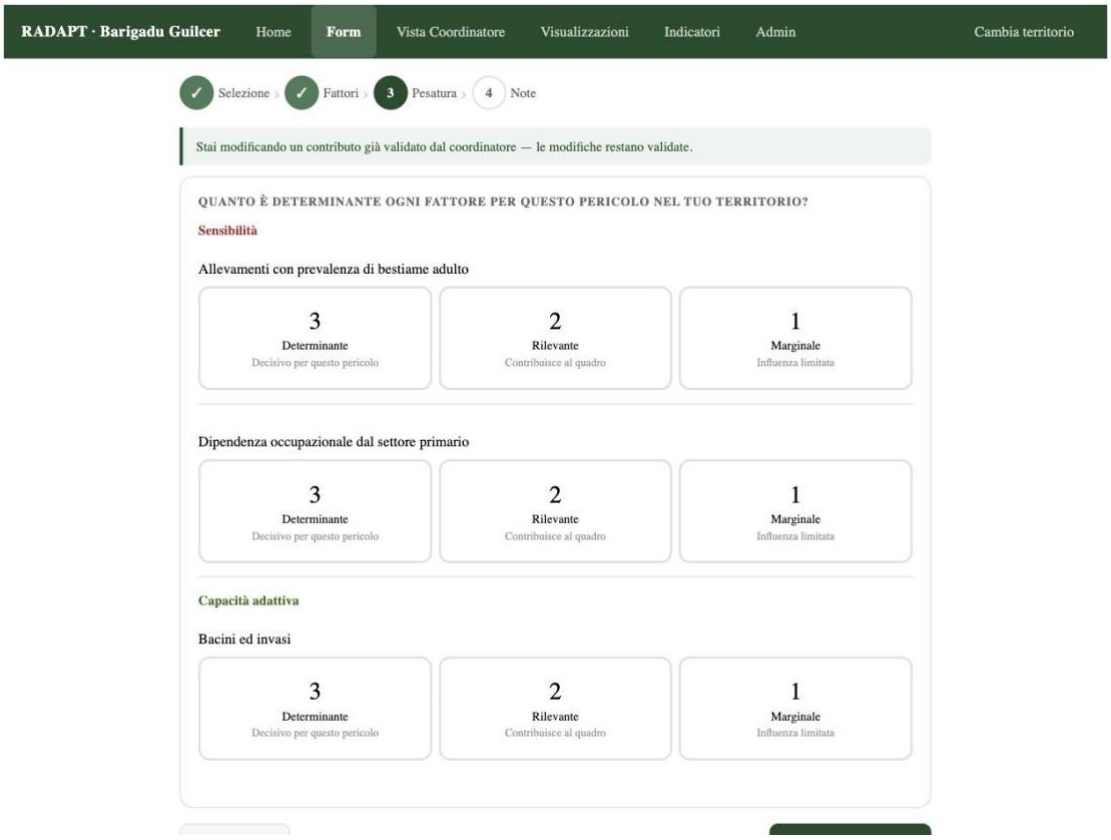

Passaggio 3 — Pesatura dei fattori di Sensibilità e Capacità adattiva.

Passaggio 4 — Note

Ultimo passaggio prima dell'invio: uno spazio per annotazioni libere sulla combinazione compilata. La bozza viene salvata automaticamente durante il lavoro; l'invio rende il contributo visibile al coordinatore per la validazione.

4. Validazione del coordinatore

Nella scheda "Vista Coordinatore" il coordinatore rivede i contributi inviati dai referenti e li valida uno per uno. La validazione di un field sblocca per quel field la Fase 2 (pesatura degli indicatori).

Un contributo già validato resta modificabile dal referente: un avviso lo segnala esplicitamente ("Stai modificando un contributo già validato dal coordinatore — le modifiche restano validate"), così da poter correggere refusi o dettagli senza dover richiedere una nuova validazione.

5. Resettare una scheda

Nel pannello Admin, tra gli strumenti riservati al coordinatore, è presente "Resetta scheda": riporta allo stato di bozza un contributo già inviato, ad esempio per farlo ricompilare da capo dopo un errore rilevante. Lo strumento mostra tutte le combinazioni presenti in libreria, comprese quelle non più attive per il territorio, per poter intervenire anche su dati storici. È un'azione da usare con attenzione, perché cancella la pesatura già registrata per quella combinazione.

6. Selezione e pesatura degli indicatori (Fase 2)

Una volta che un field è stato validato dal coordinatore, il referente può passare alla scheda "Indicatori" e scegliere, per quel field, gli indicatori quantitativi e qualitativi più adatti a misurarlo, pesandoli con la stessa logica Determinante / Rilevante / Marginale usata per i fattori.

La scheda "Indicatori" (raggiungibile anche dal menu principale) offre una vista d'insieme dello stato di avanzamento per ciascun field assegnato, raggruppato per categoria, con lo stato di ogni combinazione sistema × pericolo (per esempio "Non iniziato"):

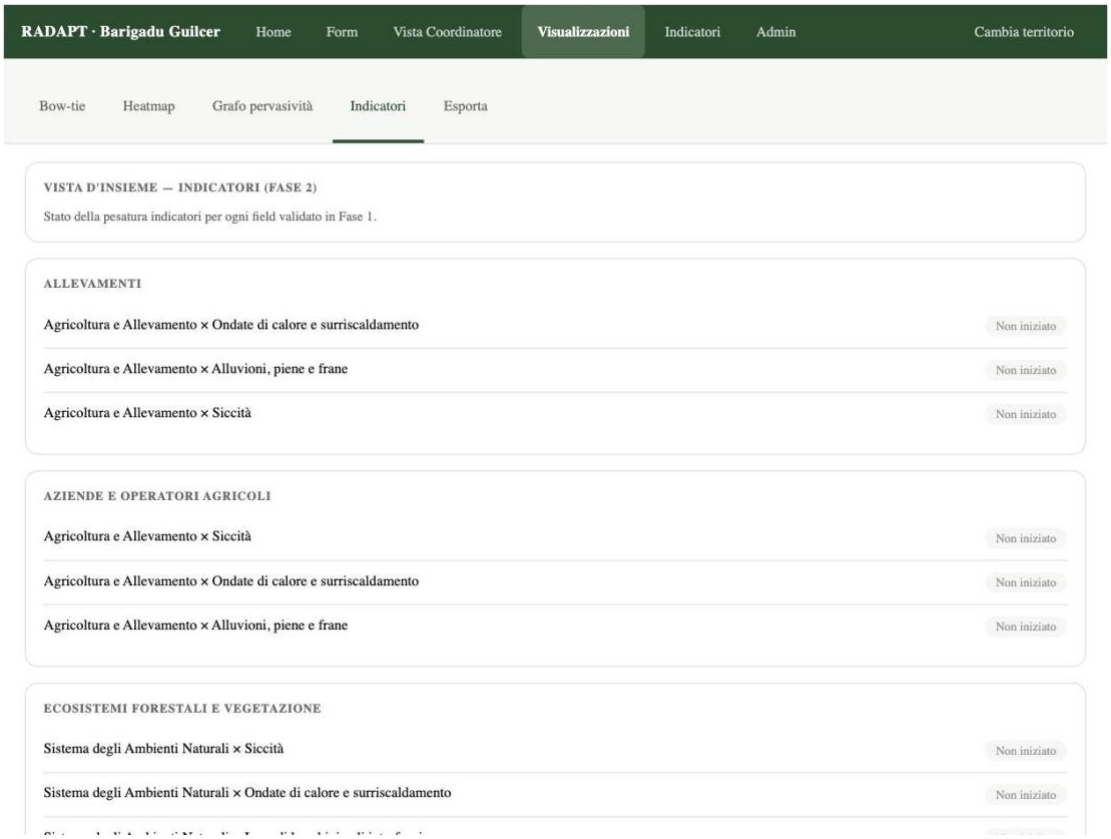

Vista d'insieme della pesatura degli indicatori, per field e combinazione.

7. Spazio commenti

Lo spazio commenti descritto al Passaggio 2 della compilazione è operativo: ogni fattore selezionato per una combinazione ha una propria discussione, visibile a tutti i referenti che lavorano su quella combinazione e al coordinatore. È pensato per chiarire un dubbio, motivare una scelta o segnalare un'incertezza senza bloccare l'avanzamento della scheda.

8. Visualizzazioni ed esportazione

La scheda "Visualizzazioni" raccoglie cinque strumenti di lettura dei dati raccolti.

Bow-tie

Per un singolo contributo (si sceglie referente e combinazione da un menu a tendina), mostra il diagramma pericolo → esposizione → vulnerabilità → rischio atteso. Nella colonna "Vulnerabilità" i fattori di Sensibilità sono segnalati come amplificanti (in rosso) e quelli di Capacità adattiva come riducenti (in verde), con il peso assegnato a ciascuno (Det· Rel· Mar·).

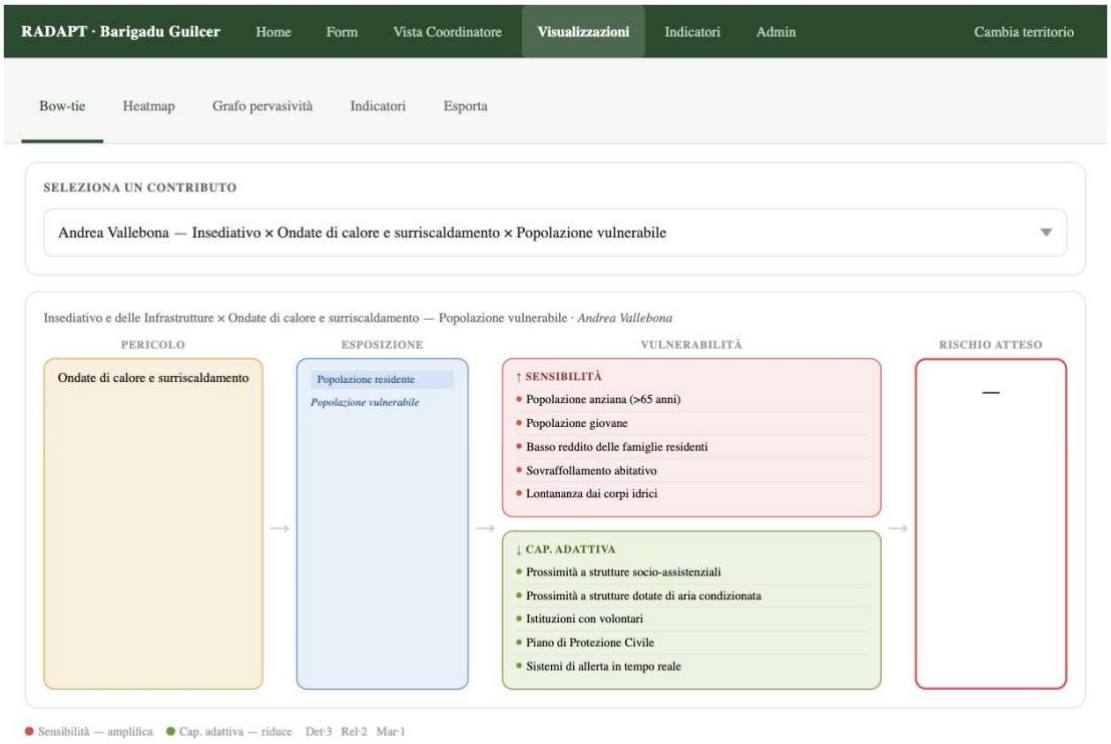

Diagramma bow-tie di un contributo: pericolo, esposizione, vulnerabilità, rischio atteso.

Heatmap

Vista sintetica del livello di rischio per ogni combinazione sistema × pericolo, con codice colore (Alto, Medio, Basso, Non valutato) e i field coinvolti elencati in ciascuna cella; cliccando su una cella si accede al dettaglio.

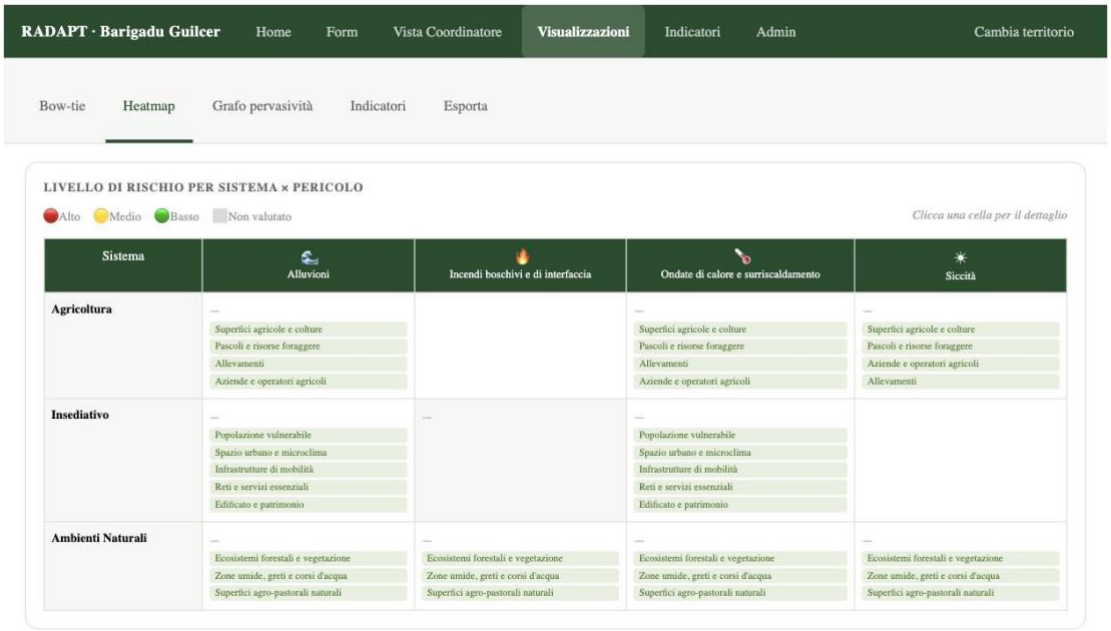

Heatmap del livello di rischio per sistema × pericolo.

Grafo di pervasività

Rappresenta graficamente quali fattori ricorrono in più field o in più sistemi (fattori "pervasivi"), con tre modalità di lettura (Fattori per field, Field correlati, Classifica fattori) e filtri per sistema e per field.

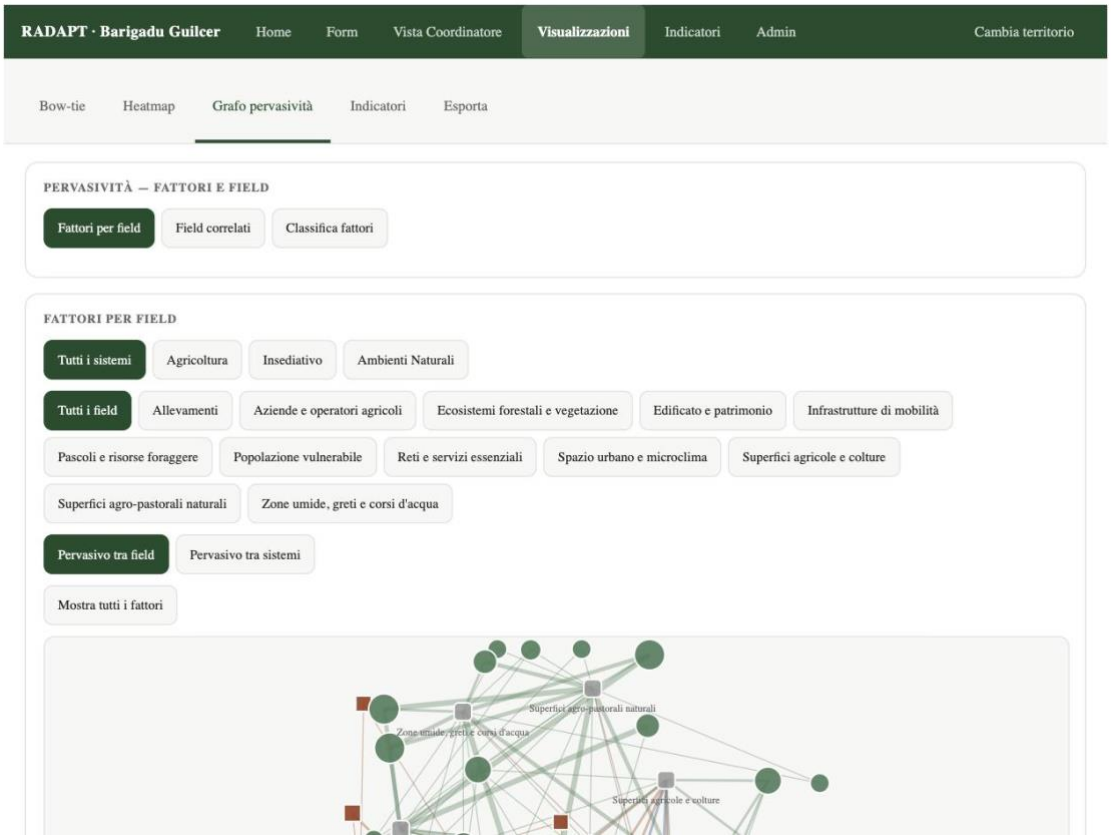

Grafo di pervasività dei fattori tra field e sistemi.

Indicatori

Vista d'insieme già descritta al punto 6, richiamata anche qui perché fa parte della stessa scheda "Visualizzazioni".

Esporta

Genera un documento scaricabile a partire dai contributi visibili, nello stesso formato delle tavole del documento di pianificazione originale. Si sceglie il Contenuto (per esempio "Catene d'impatto"), il Formato (Word .docx) e il Raggruppamento (per esempio "Per sistema × pericolo — una tavola per combinazione"), poi si genera e scarica il file.

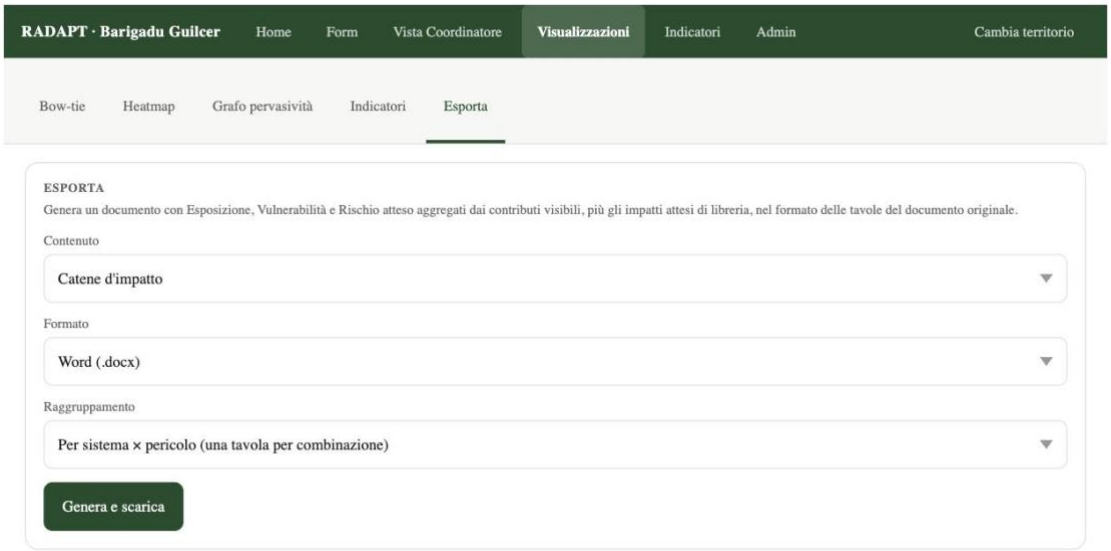

Esportazione delle catene d'impatto in un documento Word.

9. Lavorare su più territori

Chi ha accesso a più territori (per esempio come coordinatore o referente sia di Barigadu Guilcer sia, in futuro, di Comune di Sinnai) opera su un territorio alla volta per ogni sessione. Il nome del territorio attivo è sempre visibile in alto a sinistra; si cambia territorio in qualsiasi momento con "Cambia territorio", senza perdere il lavoro già salvato sull'altro.

10. Riservatezza dei dati

I dati sono separati per territorio a livello di database: chi lavora su Barigadu Guilcer non può vedere i dati di un altro territorio, e viceversa. L'accesso avviene tramite link personale, non cedibile ad altri.

> **Cosa contiene già la piattaforma per il Barigadu Guilcer**
>
> La libreria dei fattori è stata costruita confrontando le catene di impatto già elaborate per il Barigadu Guilcer con il glossario IPCC AR6 WGII (Working Group II — impatti, adattamento, vulnerabilità). Da questo lavoro derivano le 39 combinazioni sistema × pericolo × field oggi attive e assegnate ai referenti del territorio.
>
> È un punto di partenza, non un lavoro concluso: ogni field richiede comunque la descrizione, la pesatura e la validazione del referente competente. Un nuovo territorio come Comune di Sinnai parte invece senza combinazioni attive, perché il suo lavoro metodologico non è ancora iniziato — non è un errore della piattaforma, ma una scelta di progettazione: le combinazioni si attivano una per una, solo quando il territorio è pronto a lavorarci.

Parte 2 — Stato di avanzamento (luglio 2026)

Cosa manca

- Nessun controllo lato server verifica ancora che una combinazione scritta da un referente corrisponda davvero a una combinazione attiva per il territorio: un gap noto, non bloccante per l'uso ordinario.
- Le catene di impatto sono oggi costruite solo sui sistemi già coperti dalla libreria del Barigadu Guilcer; ambiti più ampi o diversi (per esempio ambienti costieri per Sinnai) richiederanno un lavoro metodologico dedicato, non ancora avviato.
- Non esiste ancora un flusso per revocare l'accesso di un utente a un territorio.
- I commenti sono oggi consultabili solo per singolo fattore; manca un elenco cronologico complessivo delle discussioni aperte.
- Il dominio radapt.org non è ancora configurato; la piattaforma è raggiungibile all'indirizzo Netlify attuale.
- Il logo utilizzato nell'interfaccia è ancora un segnaposto, non il logo di Rete Gaia.

Prossimi passi

- Presentazione della piattaforma al gruppo disciplinare, mercoledì 22 luglio 2026.
- Eventuale avvio del lavoro metodologico per il primo ambito di Comune di Sinnai, propedeutico all'attivazione delle relative combinazioni.
- Manutenzione della libreria dei fattori man mano che si aggiungono nuovi ambiti.

Cosa puoi fare con RADAPT — riepilogo

Cosa puoi fare	Dove si trova
Accedere senza password, con un link personale via email	Home
Assegnare i referenti e attivare le combinazioni per il territorio (coordinatore)	Admin
Compilare una catena di impatto: Esposizione, Sensibilità, Capacità adattiva	Form
Aggiungere un fattore specifico non presente in libreria	Form — Fattori
Discutere un fattore con un commento, anche fuori dal proprio ambito	Form — Commenti
Pesare fattori e indicatori (Determinante / Rilevante / Marginale)	Form — Pesatura, Indicatori
Validare i contributi del territorio e sbloccare la Fase 2 (coordinatore)	Vista Coordinatore
Consultare bow-tie, heatmap e grafo di pervasività	Visualizzazioni
Esportare le catene d'impatto in un documento Word	Visualizzazioni — Esporta